ARHITEKTONSKI
PROJEKTNI BIRO
Danijela Gonev-Aranđelović, pr.

D CREATIVE

Niš, ul. Janisa Janulisa br. 22 a
T: +381.60.536.4200
@: danijelaargon@gmail.com

PIB: 112238345 Matični broj: 65971330 Pretežna delatnost: 7111 - arhitektonska delatnost

0.1. NASLOVNA STRANA GLAVNE SVESKE TEHNIČKE DOKUMENTACIJE

0 – GLAVNA SVESKA

Investitor:	**"TEAM CONSTRUCTION 018" D.O.O.** **Donje Brijanje** Donje Brijanje bb, Leskovac
Objekat:	STAMBENI OBJEKAT, spratnosti Po+P+4, u Nišu, u ulici Ivana Gorana Kovačića br. 13, na katastarskoj parceli broj 2924 K.O. Niš - Pantelej
Vrsta tehničke dokumentacije:	**IDR** (Idejno rešenje)
Za građenje / izvođenje radova:	Nova gradnja
Projektant:	Arhitektonski projektni biro "D CREATIVE" Niš, Janisa Janulisa 22 a
Odgovorno lice projektanta:	Danijela Gonev-Aranđelović, pr
Potpis:	ДАНИЈЕЛА ГОНЕВ-АРАНЂЕЛОВИЋ 010554979 Sign Digitally signed by ДАНИЈЕЛА ГОНЕВ-АРАНЂЕЛОВИЋ 010554979 Sign DN: c=RS, serialNumber=PNORS-0802976735020, serialNumber=CA:RS-010554979, sn=ГОНЕВ-АРАНЂЕЛОВИЋ, givenName=ДАНИЈЕЛА, cn=ДАНИЈЕЛА ГОНЕВ-АРАНЂЕЛОВИЋ 010554979 Sign Date: 2024.12.30 14:37:01 +01'00'
Glavni projektant:	Danijela Gonev-Aranđelović, dipl. inž.arh.
Broj licence:	300A0071419
Potpis:	
Broj tehničke dokumentacije:	**2/XII-2024-0**
Mesto i datum:	Niš, 26.12.2024. godine

0.2. SADRŽAJ GLAVNE SVESKE

0.1.	Naslovna strana glavne sveske
0.2.	Sadržaj glavne sveske
0.3.	Odluka o imenovanju glavnog projektanta
0.4.	Izjava glavnog projektanta
0.5.	Sadržaj tehničke dokumentacije
0.6.	Podaci o projektantima
0.7.	Podaci o objektu i lokaciji
0.8.	Sažeti tehnički opis
0.9.	Specifikacija posebnih delova objekta
0.10.	Grafički prilozi

0.3. ODLUKA O IMENOVANJU GLAVNOG PROJEKTANTA

Na osnovu člana 128a. Zakona o planiranju i izgradnji ('Sl. glasnik RS', br. 72/2009, 81/2009 - ispr., 64/2010 - odluka US, 24/2011, 121/2012, 42/2013 - odluka US, 50/2013 - odluka US, 98/2013 - odluka US, 132/2014, 145/2014, 83/2018, 31/2019, 37/2019 - dr. zakon, 9/2020, 52/2021 i 62/2023) i odredbi Pravilnika o sadržini, načinu i postupku izrade i način vršenja kontrole tehničke dokumentacije prema klasi i nameni objekata, kao:

G L A V N I P R O J E K T A N T

za izradu (IDR) – Idejnog rešenja projekta arhitekture radi dobijanja Lokacijskih uslova za izgradnju stambenog objekta, spratnosti Po+P+4, u Nišu, ul. Ivana Gorana Kovačića br. 13, na katastarskoj parceli broj 2924 K.O. Niš-Pantelej, određuje se:

Danijela Gonev-Aranđelović, dipl.inž.arh., broj licence: 300 A00714 19

Projektant: Arhitektonski projektni biro "D CREATIVE" Niš, Janisa Janulisa 22 a

Odgovorno lice projektanta: Danijela Gonev-Aranđelović, pr

Potpis:

Broj tehničke dokumentacije: **2/XII-2024-0**

Mesto i datum: Niš, 26.12.2024. godine

0.4. IZJAVA GLAVNOG PROJEKTANTA IDEJNOG REŠENJA

Glavni projektant Idejnog rešenja projekta arhitekture radi dobijanja Lokacijskih uslova za izgradnju stambenog objekta, spratnosti Po+P+4, u Nišu, ul. Ivana Gorana Kovačića br. 13, na katastarskoj parceli broj 2924 K.O. Niš-Pantelejj,

Danijela Gonev-Aranđelović, dipl.inž.arh.

I Z J A V LJ U J E M

da su delovi idejnog rešenja međusobno usaglašeni, da podaciu glavnoj svesci odgovaraju sadržini idejnog rešenja.

0	GLAVNA SVESKA	2/XII-2024-0
1	PROJEKAT ARHITEKTURE	2/XII-2024-1

Glavni projektant IDR: Danijela Gonev-Aranđelović, dipl.inž.arh.

Broj licence: 300 A00714 19

Potpis:

Broj tehničke dokumentacije: **2/XII-2024- 0**

Mesto i datum: Niš, 26.12.2024. godine

0.5. SADRŽAJTEHNIČKEDOKUMENTACIJE

0	GLAVNA SVESKA	br: **2/XII-2024-0**
1	PROJEKAT ARHITEKTURE	br: **2/XII-2024-1**

0.6. PODACI O PROJEKTANTIMA

0. GLAVNA SVESKA

Projektant:	Arhitektonski projektni biro “D CREATIVE” Niš, Janisa Janulisa 22 a
Glavni projektant :	Danijela Gonev-Aranđelović, dipl. inž. arh.
Broj licence:	300 A00714 19
Potpis:	

1. PROJEKAT ARHITEKTURE

Projektant:	Arhitektonski projektni biro “D CREATIVE” Niš, Janisa Janulisa 22 a
Odgovorni projektant :	Danijela Gonev-Aranđelović, dipl. inž.arh.
Broj licence:	300 A00714 19
Potpis:	

0.7. OPŠTI PODACI O OBJEKTU I LOKACIJI

tip objekta:	Slobodnostojeći objekat	
kategorija objekta:	**B**	
klasifikacija pojedinih delova objekta:	učešće u ukupnoj površini objekta (%):	klasifikaciona oznaka:
	100 % stambena zgrada sa više od tri stana	112212 (klasa B)
naziv prostornog odnosno urbanističkog plana:	PGR područja gradske opštine Pantelej – I fazau Nišu ("Sl. list Grada Niša" br. 102/2012, 91/2018, 139/2022))	
mesto:	Niš	
broj katastarske parcele/spisak katastarskih parcela i katastarska opština:	2924 KO Niš-Pantelej	
broj katastarske parcele/ spisak katastarskih parcela i katastarska opština preko kojih prelaze priključci za infrastrukturu:	2924 i 3062 KO Niš-Pantelej	
broj katastarske parcele/ spisak katastarskih parcela i katastarska opština na kojoj se nalazi priključak na javnu saobraćajnicu:	2924 i 3062 KO Niš-Pantelej	

PRIKLJUČCI NA INFRASTRUKTURU:	
priključak na vodovodnu mrežu	Na gradski vodovod u ulici Ivana Gorana Kovačića, predviđeni kapacitet 1.682 l/s za sanitarnu vodu.
priključak na kanalizacionu mrežu	Na postojeću gradsku kanalizaciju za upotrebljene vode u ulici Ivana Gorana Kovačića, predviđeni kapacitet 4.893 l/s sa priključkom od Ø160 mm.
priključak na telekomunikacionu mrežu	Na postojeću telekomunikacionu trasu, predviđeni kapacitet 13 linija.
priključak na saobraćajnu mrežu	Predviđen je jedan kolsko-pešački prilaz ka parking mestima na parteru, iz ulice Ivana Gorana Kovačića.
priključak na distributivni elektroenergetski sistem	
ukupan kapacitet	Predviđen je 269,79 kW

vrsta priključka	Trajni
vrsta mernog uređaja	Sve trofazna dvotarifna brojila
način grejanja	Na električnu energiju
potrebni energetski kapaciteti za različite namene	13 stanova x 17.25 kW, 25 A. Ukupno brojila je 13 kom.
potrebni energetski kapaciteti za zajedničku potrošnju	zajednička potrošnja 1 x 11.04 kW, 16 A, lift 1 x 17.25 kW, 25 A, hidrofor 1 x 17.25kW, 25 A Ukupno brojila je 3 kom.
podaci o priključcima postojećih objekata na parcelama	broj brojila 001421 broj brojila 4377487
netipični potrošači	Nema netipičnih potrošača
potreba za većom pouzdanošću i sigurnosti u isporuci električne energije	Nema potrebe za većom pouzdanošću i sigurnosti u isporuci električne energije

OSNOVNI PODACI O OBJEKTU I LOKACIJI

dimenzije objekta:	ukupna površina parcele/parcela:	534 m^2
	ukupna BRGP nadzemno:	854.40 m^2
	ukupna BRUTO izgrađena površina:	930.31 m^2
	ukupna NETO površina:	759.66 m^2
	površina prizemlja:	73.00 m^2
	površina zemljišta pod objektom/zauzetost:	195.35 m^2
	spratnost (nadzemnih i podzemnih etaža):	podrum, prizemlje i četiri sprata
	visina objekta (venac, sleme, povučeni sprat i dr.) prema informaciji o lokaciji:	Venac i sleme +15.00 m
	apsolutna visinska kota (venac, sleme, povučeni sprat i dr.) prema informaciji o lokaciji	Venac i sleme +227.90m.n.v.
	spratna visina:	podrum 2.58 m prizemlje 2.87 m spratovi 2.87 m
	broj funkcionalnih jedinica/broj stanova:	13 stanova
	broj parking mesta:	13
materijalizacija objekta:	materijalizacija fasade:	etiks fasada
	orijentacija slemena:	-
	nagib krova:	1%, 4° i 6 °
	materijalizacija krova:	ker.pločice/krovni termopanel
procenat zelenih površina:	dato PGR-om: 25%	25% = 133.50 m^2
	u direktnom kontaktu sa tlom	10.83 % = 57.83 m^2
	uskopiramidalno stablo tuja 21x5=105 m^2	19.66 % = 105 m^2
	ukupno zelenilo	30.49 % = 162.83 m^2
procenat slobodnih površina u zajedničkom korišćenju stanara:	dato PGR-om: 20%	20% = 106.80 m^2
	na parteru van gabarita objekta	17.49% = 93.37 m^2
	na ravnom krovu	13.48 % = 2.52 m^2
	ukupno slobodnih površina	20.01% = 106.85 m^2
indeks zauzetosti:	dato PGR-om: 50%	36.58%
indeks izgrađenosti:	dato PGR-om: 1.60	1.60
predračunska vrednost objekta:	56.300.000,00RSD	

0.8. SAŽETI TEHNIČKI OPIS

uz idejno rešenje radi dobijanja Lokacijskih uslova za izgradnju stambenog objekta, spratnosti Po+P+4, u Nišu, ul. Ivana Gorana Kovačića br. 13

OPIS POSTOJEĆEG STANJA:

Predmetna parcela je izgrađena. Na njoj su izgrađeni stambeni objekat spratnosti Po+P upisan po zakonu o ozakonjenju objekata, bruto građevinske površine u osnovi 107 m^2; stambeni objekat spratnosti P izgrađen bez dozvole, bruto građevinske površine u osnovi 85 m^2; pomoćni objekat spratnosti P bruto građevinske površine u osnovi 12.85 m^2 i još jedan pomoćni objekat nadstešnica spratnosti P, bruto građevinske površine u osnovi 10.34 m^2. Svi objekti sa parcele se uklanjaju.

Novoprojektovani objekat je u slobodnostojeći.

Istočna strana građevinske parcele graniči se sa regulacionom linijom Ulice Ivana Gorana Kovačića. Sa zapadne strane graniči se sa katastarskom parcelom broj 2925 K.O. Niš - Pantelej, na kojoj je izgrađen pomoćni objekat spratnosti P na zajedničkoj međi i katastarskom parcelom broj 2923 K.O. Niš - Pantelej, na kojoj je izgrađen stambeni objekat spratnosti P na zajedničkoj međi. Sa severne strane graniči se katastarskom parcelom broj 2926/2 K.O. Niš - Pantelej na kojoj je izgrađen stambeni objekat spratnosti Po+P i još dva pomoćna objekta spratnosti P. Sa južne strane katastarskom parcelom broj 2919/1 K.O. Niš - Pantelej na kojoj je izgrađen stambeni objekat spratnosti P+1+Pk.

OPIS NOVOPROJEKTOVANOG STANJA:

Novoprojektovani objekat je istočnom fasadom postavljen iza građevinske linije, koja se po planu poklapa sa regulacionom linijom ulice Ivana Gorana Kovačića. Južnom fasadom je računajući od najisturenijeg dela objekta na udaljenosti od 3.77 do 3.90 m od međne linije sa Kp br. 2919/1 K.O. Niš – Pantelej, koja takođe ima izgrađen stambeni objekat koji nije postavljen u skladu sa planom, udaljen je 0.07-1.28 m, što je suprotno od minimalnog udaljenja koje po planu iznosi 1.5 m na delu bočnog dvorišta severne orijentacije, pa se primenjuje princip ravnopravnosti izgradnje na susednim parcelama, što podrazumeva postavljanje predmetnog objekta na minimalnoj udaljenosti od granice parcele sa susedom od ¼ maksimalne visine predviđene planom koja je 15m, 15/4=3.75 m, što je i ispoštovano. Severnom fasadom je računajući od najisturenijeg dela objekta na udaljenosti 4.41-4.45 m od međne linije sa Kp br. 2926/2 K.O. Niš – Pantelej, na kojoj je izgrađen objekat koji nije postavljen u skladu sa planom, udaljen je 2.32-2.95 m od zajedničke međe računajući od stepeništa koje savladavaju visinu od preko 0.90m i ulaze u gabarit objekta, što je suprotno od minimalnog udaljenja koje po planu iznosi 2.5 m na delu bočnog dvorišta južne orijentacije, pa se primenjuje princip ravnopravnosti izgradnje na susednim parcelama, što podrazumeva postavljanje predmetnog objekta na minimalnoj udaljenosti od granice parcele sa susedom od ¼ maksimalne visine predviđene planom koja je 15m, 15/4=3.75 m, što je i ispoštovano. Zapadnom fasadom objekat je postavljen tako da je svojim najbližim delom na minimalno 8.06 m od pomoćnog objekta koji je na zajedničkoj međi sa Kp. br. 2925 K.O. Niš - Pantelej i na minimalno 9.32 m od stambenog objekta koji je na zajedničkoj međi sa Kp. br. 2923 K.O. Niš - Pantelej

Nulta kota je usvojena ispred ulaza u objekat i iznosi 207.90 m.n.v.. Visina venca objekta je 15 m. Ispad na objektu sa istočne i zapadne strane je 1,60 m, sa severne strane u delu objekta gde ga ima 1.19 m i na južnoj strani 1.24 m od osnovnog gabarita u prizemlju. Objekat ima podrum, prizemlje i četiri sprata .

PREGLED PROJEKTOVANIH POVRŠINA PO ETAŽAMA		
Etaža	**bruto površina m^2**	**neto površina m^2**
Podrum	75.91	59.74
Prizemlje	73.00	57.52
I sprat	195.35	160.60
II sprat	195.35	160.60
III sprat	195.35	160.60
IV sprat	195.35	160.60
UKUPNO:	930.31	759.66
Bruto razvijena površina svih nadzemnih etaža:	**854.40 m^2**	
Bruto razvijena površina podruma	**75.91 m^2**	

Površina parcele:	**534**	**m^2**
Index zauzetosti:	**36.58**	**%**
Index izgrađenosti:	**1.60**	

PLNIRANA VREDNOST RADOVA 56.300.000,00 RSD

Gabarit objekta je pravougaonog oblika, čije su dimenzije i udaljenja od regulacione linije i susednih objekata u svemu u skladu sa Planom generalne regulacije područja gradske opštine Pantelej – I faza ("Službeni list Grada Niša" br. 102/2012, 91/2018, 139/2022)- u daljem tekstu Plan.

Kolski i pešački prilazi parceli predviđeni su iz ulice Ivana Gorana Kovačića sa istočne strane parcele, jedan kolsko-pešački prilaz do partera. Planirano je 13 parking mesta na parceli, koliko i ima stanova, tako da je ispunjen uslov jedno parking mesto na jedan stan. Jedno parking mesto je planirano za osobe sa invaliditetom, (5% od broja stanova je 0.65).

Ulaz u objekat, je planiran sa severne strane.

Za vertikalnu komunikaciju predviđeno je stepenište i putnički lift.

Evakuacija atmosferskih voda sa krovne ravni vrši se preko sistema horizontalnih oluka I olučnih vertikala u parcelu korisnika. Sva atmosferska voda se upija u zelenu površinu u okviru sopstvene parcele. Odvodnjavanje površinskih voda utvrđeno je nivelacionim rešenjem, odnosno, vode se odvode sa parcele slobodnim padom prema zelenim površinama u okviru parcele, i to sa najmanjim padom od ≈ 1,5%. Sve površinske vode sa predmetne građevinske parcele se usmeravaju i sakupljaju isključivo u parcelu korisnika i evakuišu na način da ne ugrožavaju susedne parcele.

STANOVI I NJHOVA OBRADA

a./ Struktura stana:

Objekat je projektovan sa 13 stana, i to:

- U prizemlju je projektovan jedan stan. Na prvom, drugom, trećem i četvrtom spratu ima po tri stana, što je ukupno 13 stanova različitih površina i struktura.

- U podrumu su predviđene stanarske ostave i ostava za higijeničara.

Površine stanova, komunikacija i ostalih prostora, odnosno površine svake prostorije ponaosob date su tabelarno u pregledu površina po osnovama podruma, prizemlja i spratova te se ovde ne opisuju.

Neto površina merena je prema zidarskim merama.
Korisna površina= neto površina umanjena za 3%.

b./ Obrada stanova

PODOVI

1. U dnevnoim sobama,prostorima za ručavanje, ostalim sobama iu predsobljimapod je od bukovog parenog ili hrastovogparketa I klase na podlozi od cementnog estriha ispod koga je data termoizolacija od stiropora. Pored zidova je postavljena parketna lajsna takođe lakirana bezbojnim lakom.
2. U kuhinjama, pod je od keramičkih pločica u cementnom malteru.
3. U sanitarnim čvorovima(kupatilima i WCima) podovisu od keramičkih pločica I klase u cementnom malteru sa hidroizolacijom.
4. Na stepeništimapredviđeno je oblaganje neklizajućim granitnim keramičkim pločicama.
5. Pod u ostavi je od keramičkih pločica u cementnom malteru.
6. Pod u podrumu je hidroizolovan, tj. projektovana je horizontalna i vertikalna hidroizolacija suterena.

ZIDOVI I PLAFONI

Svi zidovi su malterisani produžnim malterom. U svim sobama, ulazima, kuhinjama i prostorijama za ručavanje, sve zidove i plafone gletovati i bojiti u tonu po izboru investitora.

Zidovi kupatila do plafona kao i na radnim delovima kuhinje, obložiti ili su obloženi keramičkim pločicama I klase.

Zidovi u podrumu su presečeni hidroizolacijom.

STOLARIJA

Sva stolarija je po SRPS-u.Spoljna stolarija na objektu jeod Al profila, zastakljena prozorskim termopan staklom d=4+16+4 mm.Ulazna vrata u objekat su od Al profila u tonu sa spoljnom stolarijom.

Sva unutrašnja drvena stolarija je po izboru investitora, suvomontažna finalno obrađena.

BRAVARIJA

Ograda stepeništa je od metalnih profila, kao i buduća ograda terasa,i bojenau tonu po izboru investitora.

LIMARSKI RADOVI

Od limarskih radova predviđa se opšivanje pocinkovanim limom i to:

- svi bankovi na prozorima, dimnjaci, ventilacije, uvale i krovne vetar lajsne.
- horizontalni i vertikalni oluci za odvod atmosverske vode.

KONSTRUKCIJA

Konstruktivni sistem je AB skeletna zgrada sa ispunom zidovima od nenosećeg bloka d= 20 cm u produžnom malteru. MB ramovske konstrukcije kao i armiranje konstruktivnih elemenata prema statičkom proračunu.

Temeljenje objekta je izvedeno preko armirano-betonskih temeljnih traka. Temeljne trake nisu date na istoj koti fundiranja.

Zidovi podruma su od betonskog bloka sa vertikalnim serklažima.

Svi spoljašni i unutrašnjizidovi iznad podruma su d=20 i 10 cm zidani nenosećim giter blokom u produžnom malteru u svemu prema statičkom proračunu. .

Međuspratna konstrukcija je masivna krstasto-armirana ploča dp=18 cm MB 30, a iznad podruma ojačana masivna krstasto-armirana ploča dp=18 cm, MB 30.

Prema članu 61. stav 10, Zakona o smanjenjurizika od katastrofa i upravljanjuvanrednim situacijama(Sl. Glasnik RS, broj 87/2018), projektovana je ojačana tavanica nad podzemnim prostorijama d=18 cm, MB 30, koja može da izdrži urušavanje objekta prema opterećenjima iz člana 55. Pravilnika o tehničkim normativima za skloništa (Sl. list SFRJ br. 55/83).

Pregradni zidovi su od opekarskih blokova debljine 10 cm.

OBRADA FASADE

Fasada se planira u sistemu „ETICS“ shodno odredbama “Pravilnika o tehničkim zahtevima bezbednosti od požara spoljnih zidova zgrada”, predmetni objekat spada u kategoriju „V2“. Za navedenu kategoriju zgrada „V2“ u tabeli 3 definisane su potrebne karakteristike reakcije na požar za sistem najmanje Bs1d1 ili klase rekcije na požar komponenti završni sloj najmanje Bs1d1 i toplotno izolacioni sloj najmanje A2 s1d1, premetna fasada mora da zadovlji nepred navedene karakteristike.Deo fasadnih površina obložen pranim kulijerom i granitnom.

ZAGREVANJE STANOVA

Zagrevanje stanova je planirano naelektričnu energiju.

KROV

Krov je delom ravan, deo koji je planiran kao prohodni, tj. kao prostor za zajedničko korišćenje stanara, dok je ostali deo kosi krov sa pokrivačem od krovnih termopanela sa kondenz filcom.

SLOBODNE I ZELENE POVRŠINE

Zelene površine u vidu travnjaka sa niskim zelenilom prostorno predstavljaju deo partera predmetne lokacije u površini od 57.83 m², odnosno 10.83% od ukupne površine građevinske parcele. Ispod ovih zelenih površina nema podrumskih prostorija niti drugih konstruktivnih delova objekta. Visoko zelenilo tipa uspravno tanko uskopiramidalno stablozauzima 19.66%, tj. 21 stablo tuja (thuja ocidentalis f. pyramidalis) x 5 m², što je ekvivalent 105 m² zelene površine. Ukupno je 162.83 m² zelenila, izraženo u procentima 30.49 %.

Prema Planu generalne regulacije područja Gradske opštine Pantelej – I faza ("Sl. List Grada Niša", broj 102/12, 91/18 i 139/22) u slučaju nove gradnje, dogradnje, nadziđivanja i rekonstrukcije sa povećanjem broja stambenih jedinica na ukupno više od 3 nezavisne stambene jedinice, na svaki stan predvideti po jednu sadnicu stabla u oviru parcele/kompleksa ili na javnom i ostalom zemljištu u granici Plana, a prema uslovima nadležnog javnog komunalnog preduzeća. Projektom je predviđeno 21 stablo tuja u parteru, što je više od broja stanova. One su pozicionirane po obodu parcele kako bi vizuelno odvojile dvorište od susednih parcela. Postavljene su na osovinskom razmaku od minimalno 1.5 m, obzirom da je prečnik krošnje 1.5 m, na udaljenosti od granice parcele ososvinski na 0.8 i 0.9 m, kako bi stvorile vizuelnu barijeru.

Slobodne površine u zajedničkom korišćenju su planiranena na parteru, van gabarita objekta u površini od 93.37 m², što je 17.49% od površine parcele, i na krovu u površini od 13.48 m², što je 2.52% od površine parcele, tj. predviđena je zona za miran odmor stanara sa klupama za odmor i okupljanjeu ukupnoj površini od 106.85 m² tj. 20.01% od ukupne površine parcele.

ENERGETSKA EFIKASNOST

Lokacija stambenog objekta je smeštena u stambenoj zoni i projektovana je kao slobodnostojeći objekat . Objekat spratnosti Po+P+4 orjentisan je u pravcu istok-zapad.

Faktor oblika fo=A/Vo=0,39 m-1. Ovakva forma i struktura objekta obezbeđuje dobar toplotni kapacitet.

Sve dnevne prostorije u stanovima imaju prirodno osvetljenje i ventilaciju sa prozorima dimenzionisanim tako da zadovoljavaju minimume postavljene važećim propisima i standardima.

Za postizanje toplotnog komfora koristimo interakciju spoljašnjeg i unutrašnjeg prostora. Postavljanjem spoljašnje toplotne izolacije i ugradnjom kvalitetne spoljne stolarije čiji je max U=1,5 W/m^{2}K, smanjuje se temperaturna razlika između unutrašnjih površina omotača zgrade, odnosno, sprečava se velikaneuravnotežena razlika temperature površina koje zrače. Toplotni komfor je postignut oblaganjem svih spoljašnjih zidova kvalitetnim termoizlacijom debljine d=10cm, postavljanjem adekvatne termoizlacije u podu ka podrumu iu konstrukciji krova.

Vazdušni komfor – ventilacija prostora u zgradi je prirodna. Svetlosni komfor u zgradi je obezbeđen uvođenjem prirodnog svetla u prostorije za rad i boravak, kao i veštačkim osvetljenjem u pojedinim nestambenim prostorijama.

Zvučni komfor (adekvatna zvučna izolacija prostora od spoljašnjeg prostora, prihvatljiv nivo zvučnogpritiska, akustični odziv prostora...) predstavlja uslove u kojima je nivo buke u prostoriji takav da ne izaziva osećaj neprijatnosti. Za postizanje zvučnog komfora, pre svega, je

bitna dobro dimenzionisana zvučna izolacija zgrade u odnosu na nivo buke iz spoljašnjeg okruženja i od rada unutrašnjih tehničkih sistema i opreme. Na prvom mestu, zvučna izolacija se postiže dobrom toplotnom izolacijom i zaptivenošću objekta, pa se ujedno takva izolacija ponaša kao i dobar zvučni apsorber.

Po dispoziciji i konceptu objekta moguće je korišćenje pasivnih i aktivnih solarnih sistema, kao i ostalih sistema baziranih na obnovljivim izvorima energije.

KOMUNALNA INFRASTRUKTURA

Objekat je planiran sa instalacijom vodovoda i kanalizacije, elektroinstalacijom, telekomunikacionom i signalnim instalacijama, kao i mašinskom instalacijom lifta.

Ove instalacije biće priključene na gradske mreže preko šahti odnosno ormarića, prema uslovima Javnih preduzeća. Za sve instalacije dobiće su uslovi za projektovanje i priključenje JP i oni će biti sastavni deo Lokacijskih uslova.

Priključak na javnu saobraćajnicu predviđen je kolsko-pešačkim prilazom iz ulice Ivana Gorana Kovačića.

Glavni projektant:

Danijela Gonev-Aranđelović, dipl. inž. arh.

0.9. SPECIFIKACIJA POSEBNIH DELOVA

ETAŽA	FUNKCIONALNA JEDINICA	VRSTA DELA OBJEKTA	NETO POVRŠINA	
Prizemlje	Stan 1	posebni deo	42.26 m²	42.26 m²
I sprat	Stan 2	posebni deo	53.62 m²	
	Stan 3	posebni deo	65.09 m²	
	Stan 4	posebni deo	31.44 m²	150.15 m²
II sprat	Stan 5	posebni deo	55.12 m²	
	Stan 6	posebni deo	51.62 m²	
	Stan 7	posebni deo	69.12 m²	150.15 m²
III sprat	Stan 8	posebni deo	55.12 m²	
	Stan 9	posebni deo	51.62 m²	
	Stan 10	posebni deo	69.12 m²	150.15 m²
IV sprat	Stan 11	posebni deo	55.12 m²	
	Stan 12	posebni deo	51.62 m²	
	Stan 13	posebni deo	69.12 m²	150.15 m²
Ukupna površina stanova				642.86 m²

0.10. GRAFIČKI PRILOZI

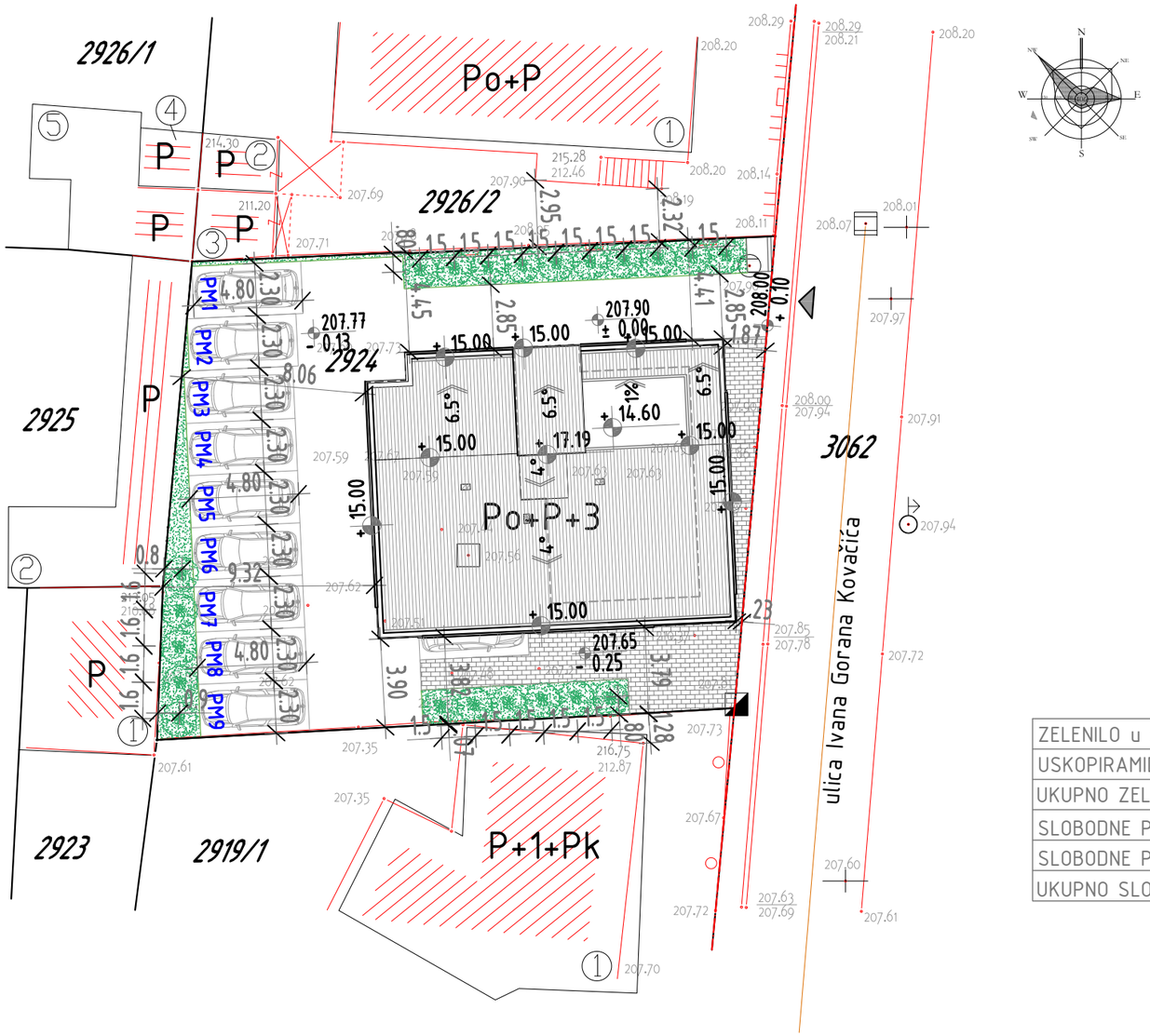

L E G E N D A:

- Katastarsko stanje
- Faktičko stanje
- Topografski znaci
- RL=GL
- Gabarit podruma
- Zelene površine
- Slobodne površine
- Parking mesto
- Uskopiramidalno stablo-tuja
- Kontejner za odlaganje smeća
- Kolsko-pešački prilaz
- Ulaz u objekat
- 207.90 ± 0.00 Nulta kota terena

ZELENILO u direktnom kontaktu sa tlom	57.83m^2	10.83%
USKOPIRAMIDALNA STABLA-TUJA 21 komadx5=105m^2	105m^2	19.66%
UKUPNO ZELENILO	162.83m^2	30.49%
SLOBODNE POVRŠINE PARTER	93.37m^2	17.49%
SLOBODNE POVRŠINE RAVAN KROV	13.48m^2	2.52%
UKUPNO SLOBODNE POVRŠINE	106.85m^2	20.01%

SITUACIONI PLAN SA OSNOVOM KROVA

Oznaka: IDR	Projekat: 0 - GLAVNA SVESKA		Registarski broj: 2/XII-2024-0
Glavni projektant: dipl.inž.arh. Danijela Gonev-Aranđelović broj licence 300 A00714 19		Investitor: "TEAM CONSTRUCTION 018" DOO Donje Brijanje, Donje Brijanje bb, Leskovac	
Odgovorni projektant: dipl.inž.arh. Danijela Gonev-Aranđelović broj licence 300 A00714 19		Objekat: STAMBENI OBJEKAT, Po+P+4, u Nišu, u ul. Ivana Gorana Kovačića br.13 , na k.p. br. 2924 KO Niš-Pantelej	
		Sadržaj: SITUACIONI PLAN	
Saradnik:		Datum: 12.2024. god.	Razmera: 1:250 / List: 1

ARHITEKTONSKI PROJEKTNI BIRO
D CREATIVE
Danijela Gonev-Aranđelović PR
NIŠ, Janisa Janulisa 22a
T: +381.60.536.4200

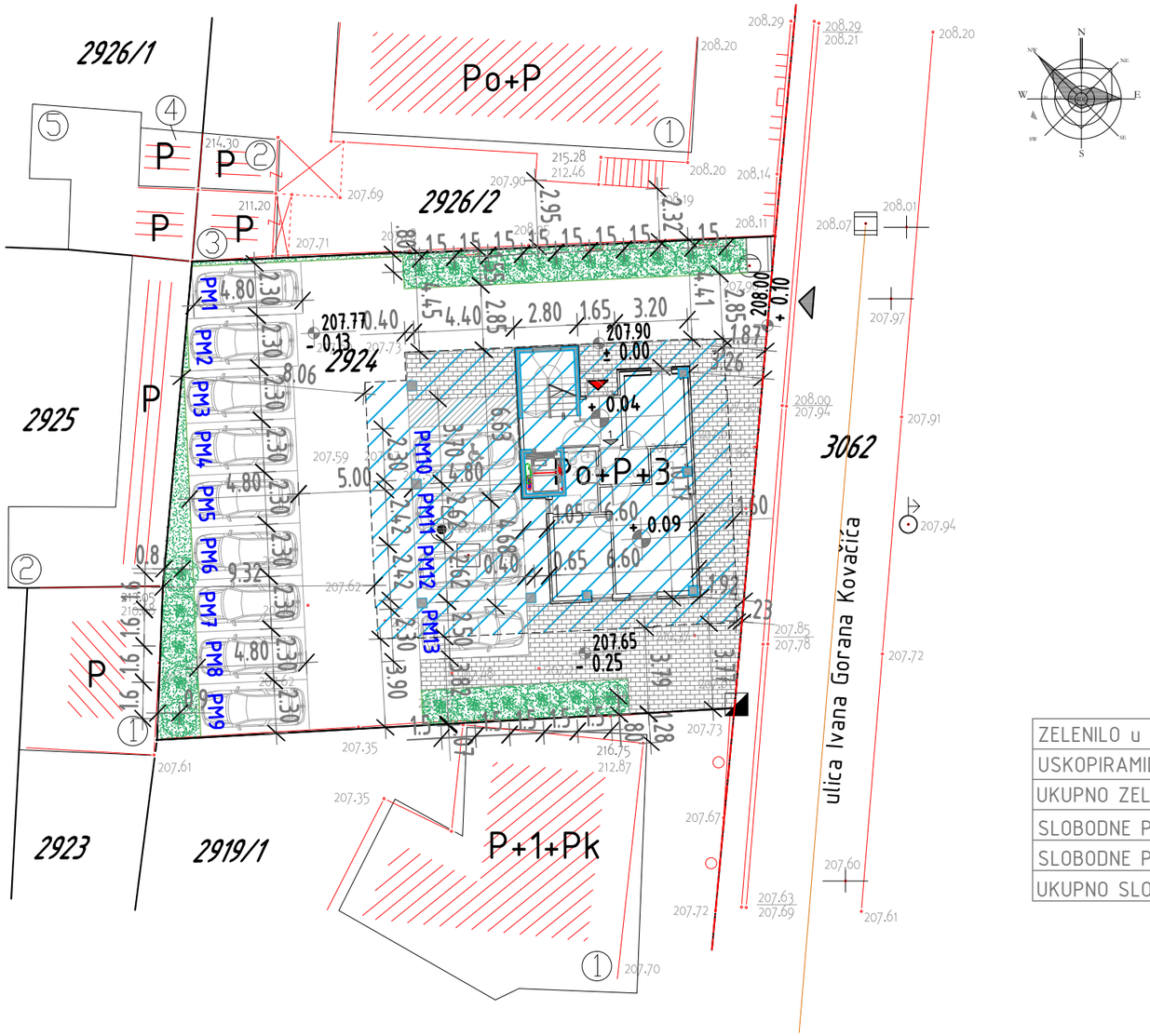

L E G E N D A:

- Katastarsko stanje
- Faktičko stanje
- Topografski znaci
- RL=GL
- Gabarit podruma
- Gabarit spratova
- Zelene površine
- Slobodne površine
- Parking mesto
- Uskopiramidalno stablo-tuja
- Kontejner za odlaganje smeća
- Kolsko-pešački prilaz
- Ulaz u objekat
- 207.90 ± 0.00 Nulta kota terena

ZELENILO u direktnom kontaktu sa tlom	57.83m²	10.83%
USKOPIRAMIDALNA STABLA-TUJA 21 komadx5=105m²	105m²	19.66%
UKUPNO ZELENILO	162.83m²	30.49%
SLOBODNE POVRŠINE PARTER	93.37m²	17.49%
SLOBODNE POVRŠINE RAVAN KROV	13.48m²	2.52%
UKUPNO SLOBODNE POVRŠINE	106.85m²	20.01%

SITUACIONI PLAN SA OSNOVOM PRIZEMLJA

Oznaka: IDR	Projekat: 0 - GLAVNA SVESKA	Registarski broj: 2/XII-2024-0	ARHITEKTONSKI PROJEKTNI BIRO
Glavni projektant: dipl.inž.arh. Danijela Gonev-Aranđelović broj licence 300 A00714 19	Investitor: "TEAM CONSTRUCTION 018" DOO Donje Brijanje, Donje Brijanje bb, Leskovac		D CREATIVE
	Objekat: STAMBENI OBJEKAT, Po+P+4, u Nišu u ul. Ivana Gorana Kovačića br.13 , na k.p. br. 2924 KO Niš-Pantelej		Danijela Gonev-Aranđelović PR
Odgovorni projektant: dipl.inž.arh. Danijela Gonev-Aranđelović broj licence 300 A00714 19	Sadržaj: SITUACIONI PLAN		NIŠ, Janisa Janulisa 22a
Saradnik:	Datum: 12.2024. god. / Razmera: 1:250	List: 2	T: +381.60.536.4200

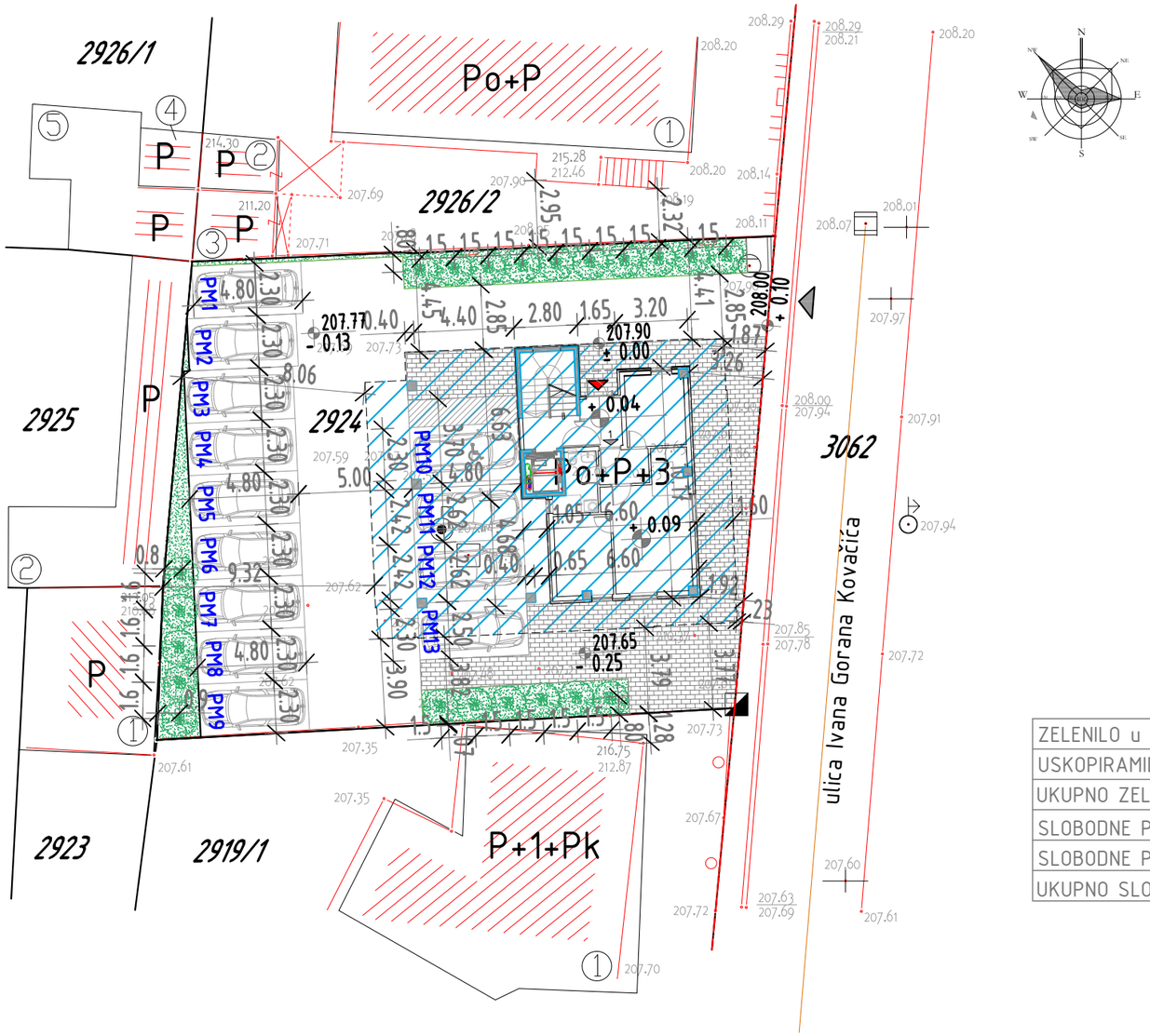

L E G E N D A:

- Katastarsko stanje
- Faktičko stanje
- Topografski znaci
- RL=GL
- Gabarit podruma
- Gabarit spratova
- Zelene površine
- Slobodne površine
- Parking mesto
- Uskopiramidalno stablo-tuja
- Kontejner za odlaganje smeća
- Kolsko-pešački prilaz
- Ulaz u objekat
- 207.90 ± 0.00 Nulta kota terena

ZELENILO u direktnom kontaktu sa tlom	57.83m²	10.83%
USKOPIRAMIDALNA STABLA-TUJA 21 komadx5=105m²	105m²	19.66%
UKUPNO ZELENILO	162.83m²	30.49%
SLOBODNE POVRŠINE PARTER	93.37m²	17.49%
SLOBODNE POVRŠINE RAVAN KROV	13.48m²	2.52%
UKUPNO SLOBODNE POVRŠINE	106.85m²	20.01%

SITUACIONO-NIVELACIONI PLAN SA SAOBRAĆAJNIM REŠENJEM

Oznaka: IDR	Projekat: 0 - GLAVNA SVESKA	Registarski broj: 2/XII-2024-0	ARHITEKTONSKI PROJEKTNI BIRO
Glavni projektant: dipl.inž.arh. Danijela Gonev-Aranđelović broj licence 300 A00714 19	Investitor: "TEAM CONSTRUCTION 018" DOO Donje Brijanje, Donje Brijanje bb, Leskovac		D CREATIVE
Odgovorni projektant: dipl.inž.arh. Danijela Gonev-Aranđelović broj licence 300 A00714 19	Objekat: STAMBENI OBJEKAT, Po+P+4, u Nišu, u ul. Ivana Gorana Kovačića br.13 , na k.p. br. 2924 KO Niš-Pantelej		Danijela Gonev-Aranđelović PR
	Sadržaj: SITUACIONI PLAN		NIŠ, Janisa Janulisa 22a
Saradnik:	Datum: 12.2024. god.	Razmera: 1:250 / List: 3	T: +381.60.536.4200

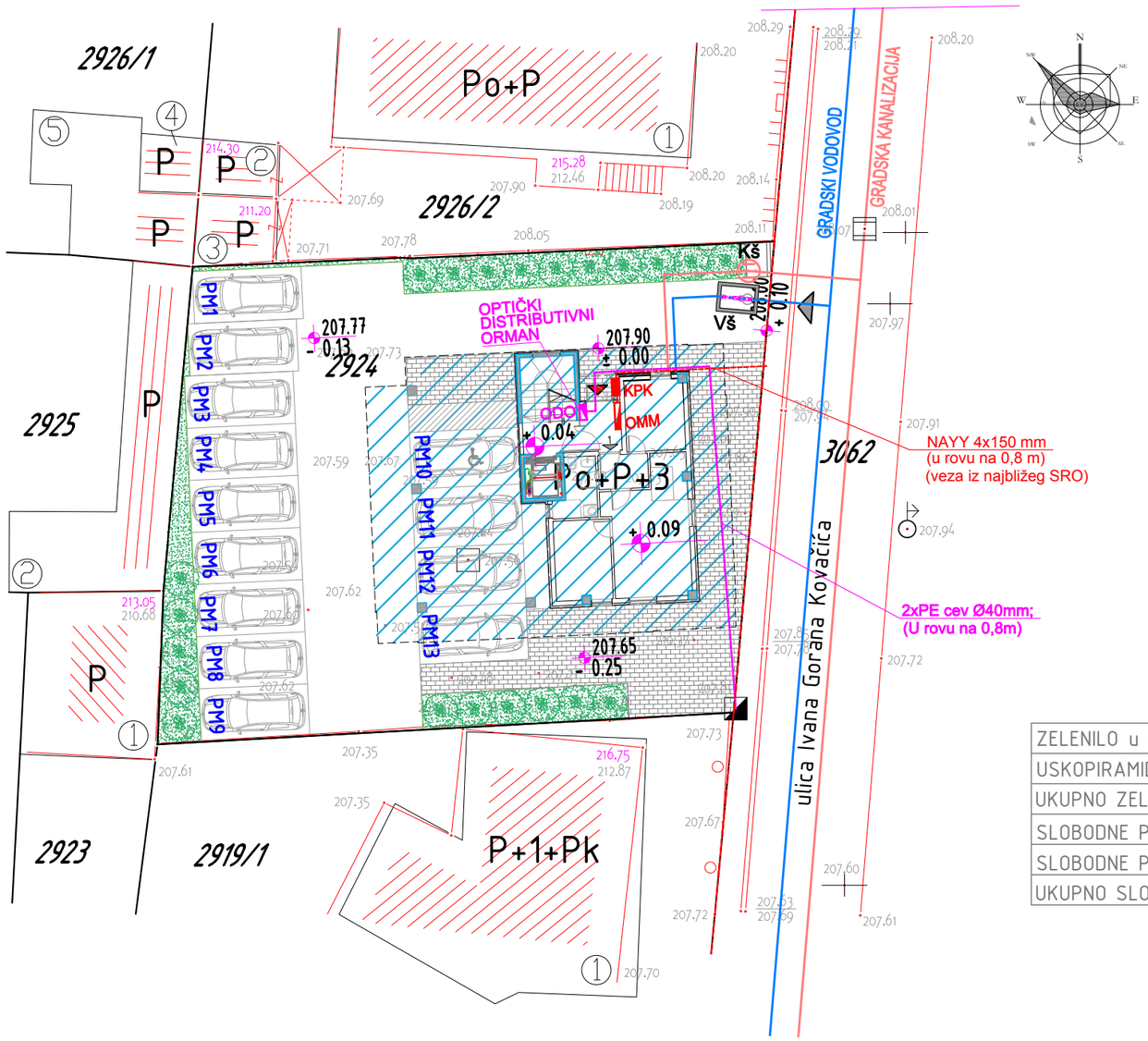

L E G E N D A:

- Katastarsko stanje
- Faktičko stanje
- Topografski znaci
- RL=GL
- Gabarit podruma
- Gabarit prizemlja
- Gabarit spratova
- Zelene površine
- Slobodne površine
- Parking mesto
- Uskopiramidalno stablo-tuja
- Kontejner za odlaganje smeća
- Kolsko-pešački prilaz
- Ulaz u objekat
- 207.90 ± 0.00 Nulta kota terena

ZELENILO u direktnom kontaktu sa tlom	57.83m²	10.83%
USKOPIRAMIDALNA STABLA- TUJA 21 komadx5=105m²	105m²	19.66%
UKUPNO ZELENILO	162.83m²	30.49%
SLOBODNE POVRŠINE PARTER	93.37m²	17.49%
SLOBODNE POVRŠINE RAVAN KROV	13.48m²	2.52%
UKUPNO SLOBODNE POVRŠINE	106.85m²	20.01%

SINHRON PLAN SA PRIKAZOM KOMUNALNE INFRASTRUKTURE

Oznaka: IDR	Projekat: 0 - GLAVNA SVESKA		Registarski broj: 2/XII-2024-0
Glavni projektant: dipl.inž.arh. Danijela Gonev-Aranđelović broj licence 300 A00714 19		Investitor: "TEAM CONSTRUCTION 018" DOO Donje Brijanje Donje Brijanje bb, Leskovac	
Odgovorni projektant: dipl.inž.arh. Danijela Gonev-Aranđelović broj licence 300 A00714 19		Objekat: STAMBENI OBJEKAT, Po+P+4, u Nišu u ul. Ivana Gorana Kovačića br.13 , na k.p. br. 2924 KO Niš-Pantelej	
		Sadržaj: SITUACIONI PLAN	
Saradnik:		Datum: 12.2024. god.	Razmera: 1:250 / List: 4

ARHITEKTONSKI PROJEKTNI BIRO
D CREATIVE
Danijela Gonev-Aranđelović PR
NIŠ, Janisa Janulisa 22a
T: +381.60.536.4200

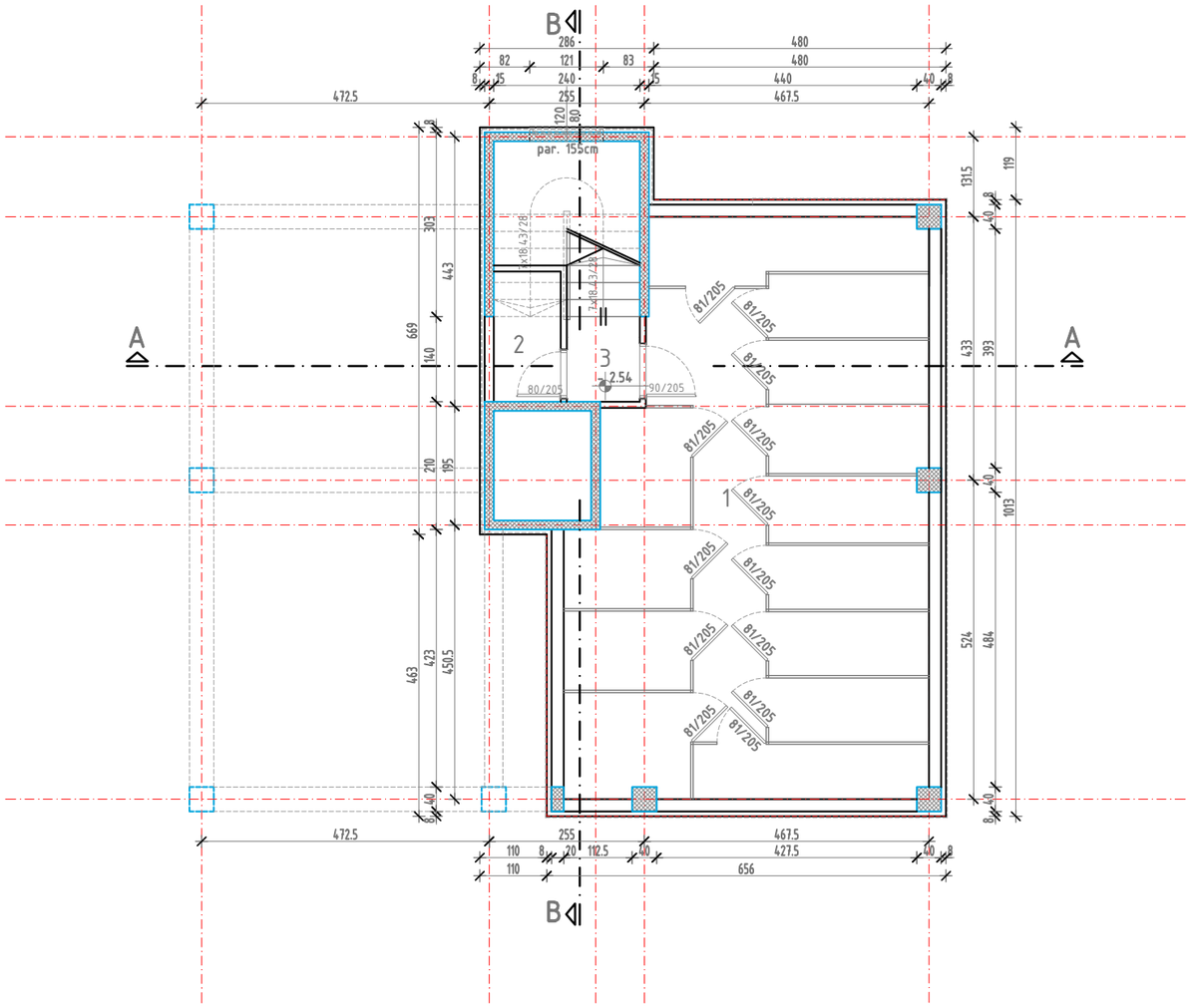

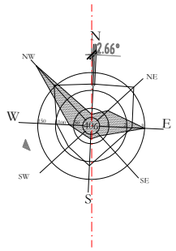

Br.	NAMENA PROSTORIJA	P(m²)	O(m)	Vrsta poda
1	STANARSKE OSTAVE	51.66	31.94	ker.pločice
2	OSTAVA HIGIJENIČAR	2.35	6.48	ker.pločice
3	STEPENIŠTE	7.58	13.36	cem.košulj.
UKUPNO:		61.59		
-3% :		59.74		
Pneto = 59.74 m²				
Pbruto = 75.91 m²				

NAPOMENA: Bruto razvijena građevinska površina iskazana je u skladu sa Pravilnikom o energetskoj efikasnosti zgrada (Službeni glasnika RS, br. 61/2011., član 2. tačka 3):
"U bruto građevinsku površnu ne računaju se površine u okviru sistema dvostrukih fasada, staklenika, površine koje čine termički omotač zgrade u bruto razvijenu građevinsku površinu ne obračunava se kod heterogenih zidova debljina termoizolacije preko 5 cm, a kod homogenih zidova debljina zida veća od 30 cm uz postizanje, ovim pravilnikom propisanih uslova energetske efikasnosti zgrade."

OSNOVA PODRUMA

Oznaka: IDR	Projekat: 0 - GLAVNA SVESKA	Registarski broj: 2/XII-2024-0	ARHITEKTONSKI PROJEKTNI BIRO
Glavni projektant: dipl.inž.arh. Danijela Gonev-Aranđelović broj licence 300 A00714 19	Investitor: "TEAM CONSTRUCTION 018" DOO Donje Brijanje Donje Brijanje bb, Leskovac		D CREATIVE
Odgovorni projektant: dipl.inž.arh. Danijela Gonev-Aranđelović broj licence 300 A00714 19	Objekat: STAMBENI OBJEKAT, Po+P+4, u Nišu u ul. Ivana Gorana Kovačića br.13 , na k.p. br. 2924 KO Niš-Pantelej		Danijela Gonev-Aranđelović PR
	Sadržaj: OSNOVA PODRUMA		NIŠ, Janisa Janulisa 22a
Saradnik:	Datum: 12.2024. god.	Razmera: 1:100 / List: 5	T: +381.60.536.4200

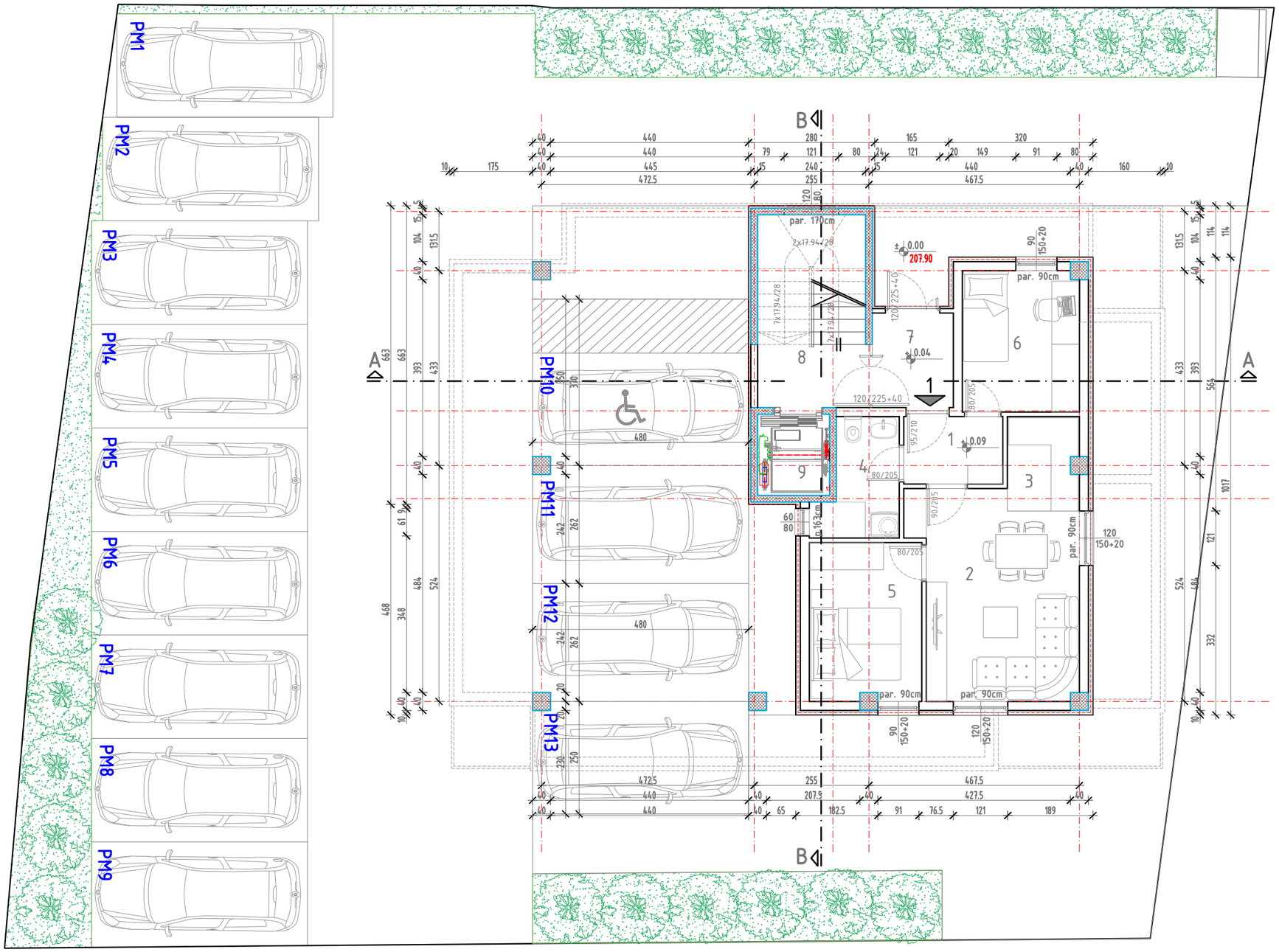

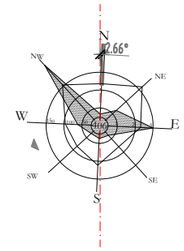

Br.	NAMENA PROSTORIJA	STAN 1		Vrsta poda
		P(m²)	O(m)	
1	PREDSOBLJE	3.30	7.40	parket
2	DNEVNA SOBA SA TRPEZARIJOM	15.79	17.26	parket
3	KUHINJA	3.28	7.80	ker.pločice
4	KUPATILO	4.26	9.40	ker.pločice
5	SOBA	8.82	12.06	parket
6	SOBA	8.12	11.48	parket
UKUPNO:		43.57		
-3% :		42.26		
7	VETROBRAN	3.78	7.80	ker.pločice
8	STEPENIŠTE	10.41	13.56	ker.pločice
9	LIFT	1.54	5.00	/
UKUPNO:		15.73		
-3% :		15.26		
Pneto = 42.26+15.26 = 57.52 m²				
Pbruto = 73.00 m²				

NAPOMENA: Bruto razvijena građevinska površina iskazana je u skladu sa Pravilnikom o energetskoj efikasnosti zgrada (Službeni glasnika RS, br. 61/2011., član 2. tačka 3):
"U bruto građevinsku površnu ne računaju se površine u okviru sistema dvostrukih fasada, staklenika, površine koje čine termički omotač zgrade u bruto razvijenu građevinsku površinu ne obračunava se kod heterogenih zidova debljina termoizolacije preko 5 cm, a kod homogenih zidova debljina zida veća od 30 cm uz postizanje, ovim pravilnikom propisanih uslova energetske efikasnosti zgrade."

OSNOVA PRIZEMLJA

Oznaka: IDR	Projekat: 0 - GLAVNA SVESKA	Registarski broj: 2/XII-2024-0	ARHITEKTONSKI PROJEKTNI BIRO
Glavni projektant: dipl.inž.arh. Danijela Gonev-Aranđelović broj licence 300 A00714 19	Investitor: "TEAM CONSTRUCTION 018" DOO Donje Brijanje, Donje Brijanje bb, Leskovac		D CREATIVE
Odgovorni projektant: dipl.inž.arh. Danijela Gonev-Aranđelović broj licence 300 A00714 19	Objekat: STAMBENI OBJEKAT, Po+P+4, u Nišu u ul. Ivana Gorana Kovačića br.13 , na k.p. br. 2924 KO Niš-Pantelej		Danijela Gonev-Aranđelović PR
	Sadržaj: OSNOVA PRIZEMLJA		NIŠ, Janisa Janulisa 22a
Saradnik:	Datum: 12.2024. god.	Razmera: 1:100 / List: 6	T: +381.60.536.4200

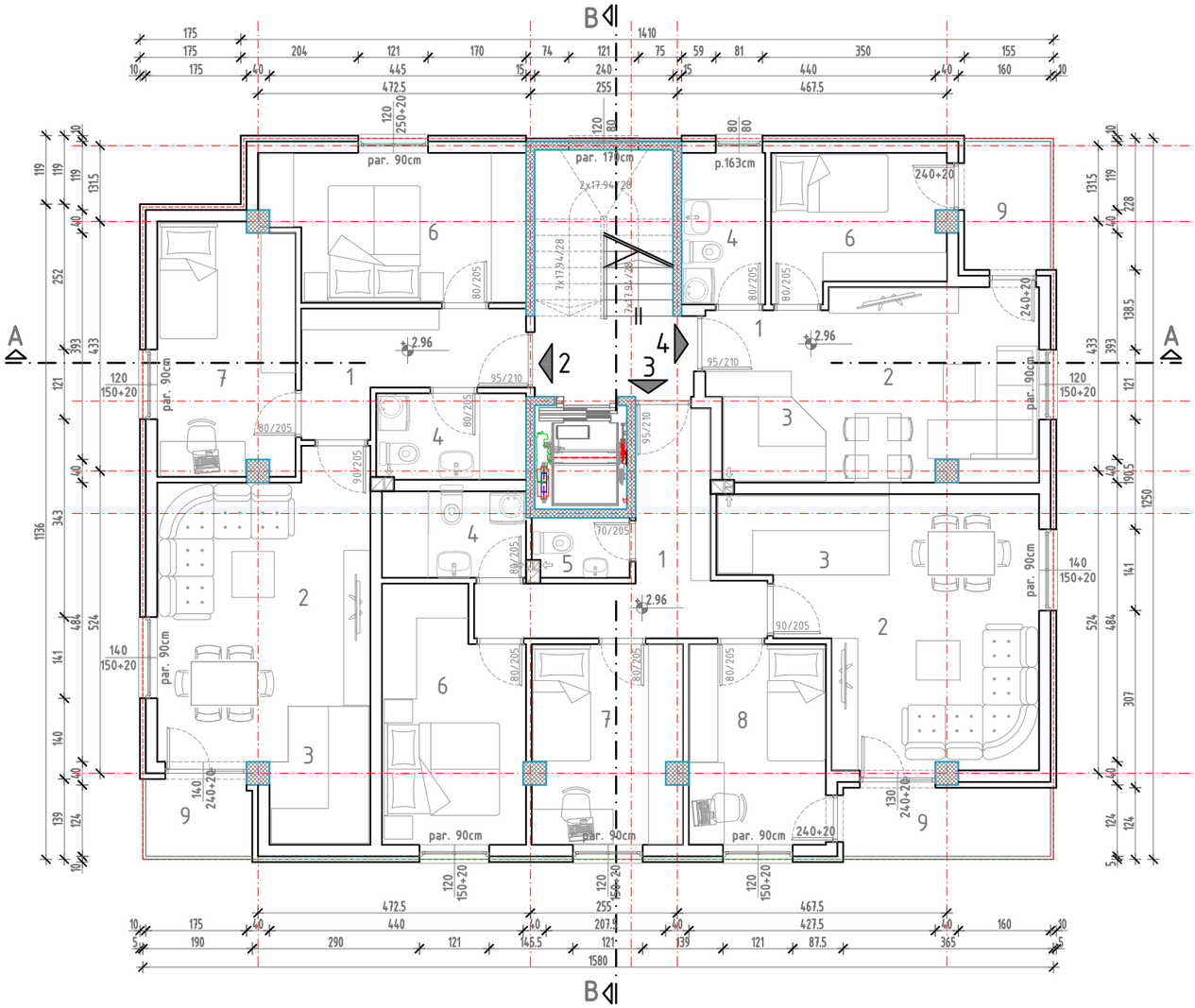

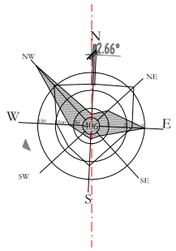

Br.	NAMENA PROSTORIJA	STAN 2 (5, 8, 11)		STAN 3 (6, 9, 12)		STAN 4 (7, 10, 13)		Vrsta poda
		P(m²)	O(m)	P(m²)	O(m)	P(m²)	O(m)	
1	PREDSOBLJE	6.44	12.36	8.83	7.40	3.21	7.28	parket
2	DNEVNA SOBA SA TRPEZARIJOM	17.30	18.36	16.91	17.26	12.47	15.82	parket
3	KUHINJA	3.82	8.20	4.19	7.80	2.49	6.23	ker.pločice
4	KUPATILO	3.88	8.20	3.75	9.40	3.81	8.16	ker.pločice
5	WC	/	/	1.72	9.40	/	/	ker.pločice
6	SOBA	10.98	14.40	10.27	12.06	7.08	11.76	parket
7	SOBA	10.35	14.26	8.89	11.48	/	/	parket
8	SOBA	/	1/	8.26	11.48	/	/	parket
9	TERASA	2.51	6.48	4.28	9.40	3.35	7.46	ker.pločice
	UKUPNO:	55.28		67.10		32.41		
	-3% :	53.62		65.09		31.44		
10	STEPENIŠTE	10.77	14.08					ker.pločice
11	LIFT	/	/					/
	UKUPNO:	10.77						
	-3% :	10.45						
	Pneto = 53.62+65.09+31.44+10.45 = 160.60 m²							
	Pbruto = 195.35 m²							

NAPOMENA: Bruto razvijena građevinska površina iskazana je u skladu sa Pravilnikom o energetskoj efikasnosti zgrada (Službeni glasnika RS, br. 61/2011., član 2. tačka 3):
"U bruto građevinsku površnu ne računaju se površine u okviru sistema dvostrukih fasada, staklenika, površine koje čine termički omotač zgrade u bruto razvijenu građevinsku površinu ne obračunava se kod heterogenih zidova debljina termoizolacije preko 5 cm, a kod homogenih zidova debljina zida veća od 30 cm uz postizanje, ovim pravilnikom propisanih uslova energetske efikasnosti zgrade."

OSNOVA I,II,III i IV SPRATA

Oznaka: IDR	Projekat: 0 - GLAVNA SVESKA	Registarski broj: 2/XII-2024-0	ARHITEKTONSKI PROJEKTNI BIRO
Glavni projektant: dipl.inž.arh. Danijela Gonev-Aranđelović broj licence 300 A00714 19	Investitor: "TEAM CONSTRUCTION 018" DOO Donje Brijanje, Donje Brijanje bb, Leskovac		D CREATIVE
Odgovorni projektant: dipl.inž.arh. Danijela Gonev-Aranđelović broj licence 300 A00714 19	Objekat: STAMBENI OBJEKAT, Po+P+4, u Nišu, u ul. Ivana Gorana Kovačića br.13 , na k.p. br. 2924 KO Niš-Pantelej		Danijela Gonev-Aranđelović PR
	Sadržaj: OSNOVA I,II,III i IV SPRATA		NIŠ, Janisa Janulisa 22a
Saradnik:	Datum: 12.2024. god.	Razmera: 1:100 / List: 7	T: +381.60.536.4200

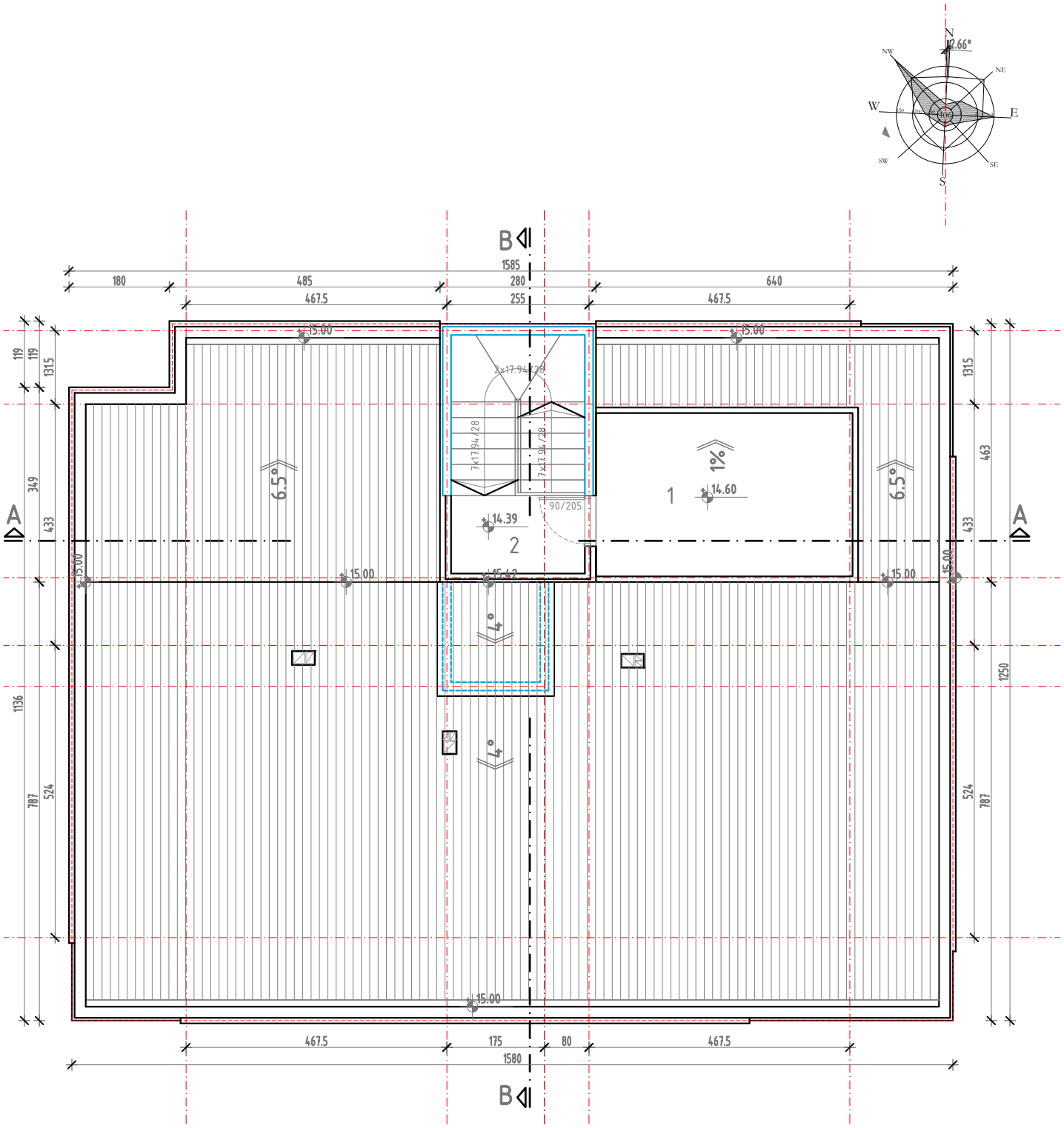

Br.	NAMENA PROSTORA	P (m²)	Vrsta poda
1	SLOBODNA POVRŠINA U ZAJEDNIČKOM KORIŠĆENJU STANARA - PROHODAN KROV	13.48	ker.pločice
2	STEPENIŠTE	10.27	ker.pločice
	UKUPNO:	23.75	

OSNOVA PROHODNE TERASE

Oznaka: IDR	Projekat: 0 - GLAVNA SVESKA	Registarski broj: 2/XII-2024-0	ARHITEKTONSKI PROJEKTNI BIRO
Glavni projektant: dipl.inž.arh. Danijela Gonev-Aranđelović broj licence 300 A00714 19	Investitor: "TEAM CONSTRUCTION 018" DOO Donje Brijanje, Donje Brijanje bb, Leskovac		D CREATIVE
Odgovorni projektant: dipl.inž.arh. Danijela Gonev-Aranđelović broj licence 300 A00714 19	Objekat: STAMBENI OBJEKAT, Po+P+4, u Nišu u ul. Ivana Gorana Kovačića br.13 , na k.p. br. 2924 KO Niš-Pantelej		Danijela Gonev-Aranđelović PR
	Sadržaj: OSNOVA KROVNIH RAVNI		NIŠ, Janisa Janulisa 22a
Saradnik:	Datum: 12.2024. god.	Razmera: 1:100 / List: 8	T: +381.60.536.4200

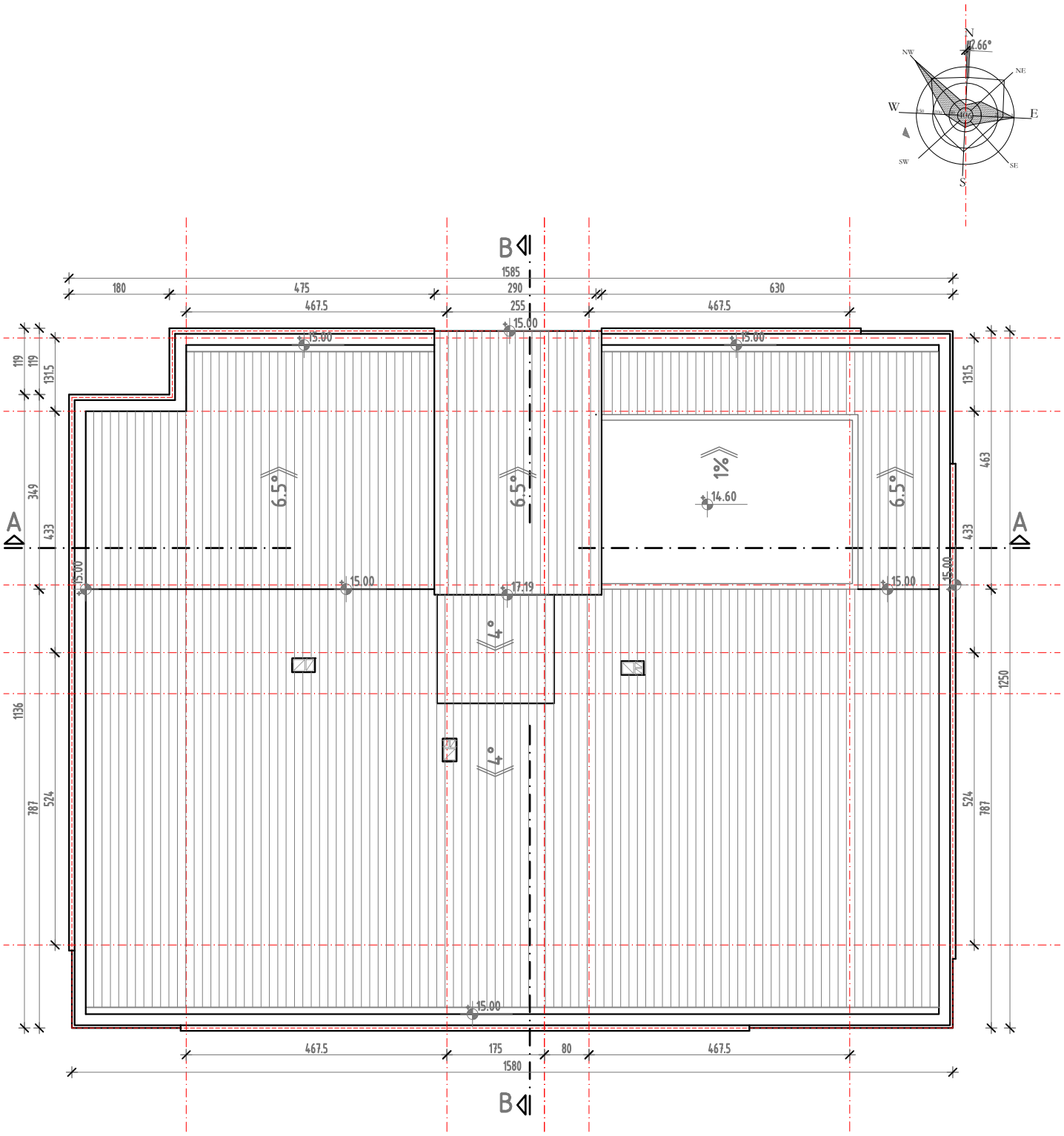

OSNOVA KROVNIH RAVNI

Oznaka: IDR	Projekat: 0 - GLAVNA SVESKA	Registarski broj: 2/XII-2024-0	ARHITEKTONSKI PROJEKTNI BIRO
Glavni projektant: dipl.inž.arh. Danijela Gonev-Aranđelović broj licence 300 A00714 19		Investitor: "TEAM CONSTRUCTION 018" DOO Donje Brijanje Donje Brijanje bb, Leskovac	D CREATIVE
Odgovorni projektant: dipl.inž.arh. Danijela Gonev-Aranđelović broj licence 300 A00714 19		Objekat: STAMBENI OBJEKAT, Po+P+4, u Nišu u ul. Ivana Gorana Kovačića br.13 , na k.p. br. 2924 KO Niš-Pantelej	Danijela Gonev-Aranđelović PR
		Sadržaj: OSNOVA KROVNIH RAVNI	NIŠ, Janisa Janulisa 22a
Saradnik:		Datum: 12.2024. god. / Razmera: 1:100 / List: 9	T: +381.60.536.4200

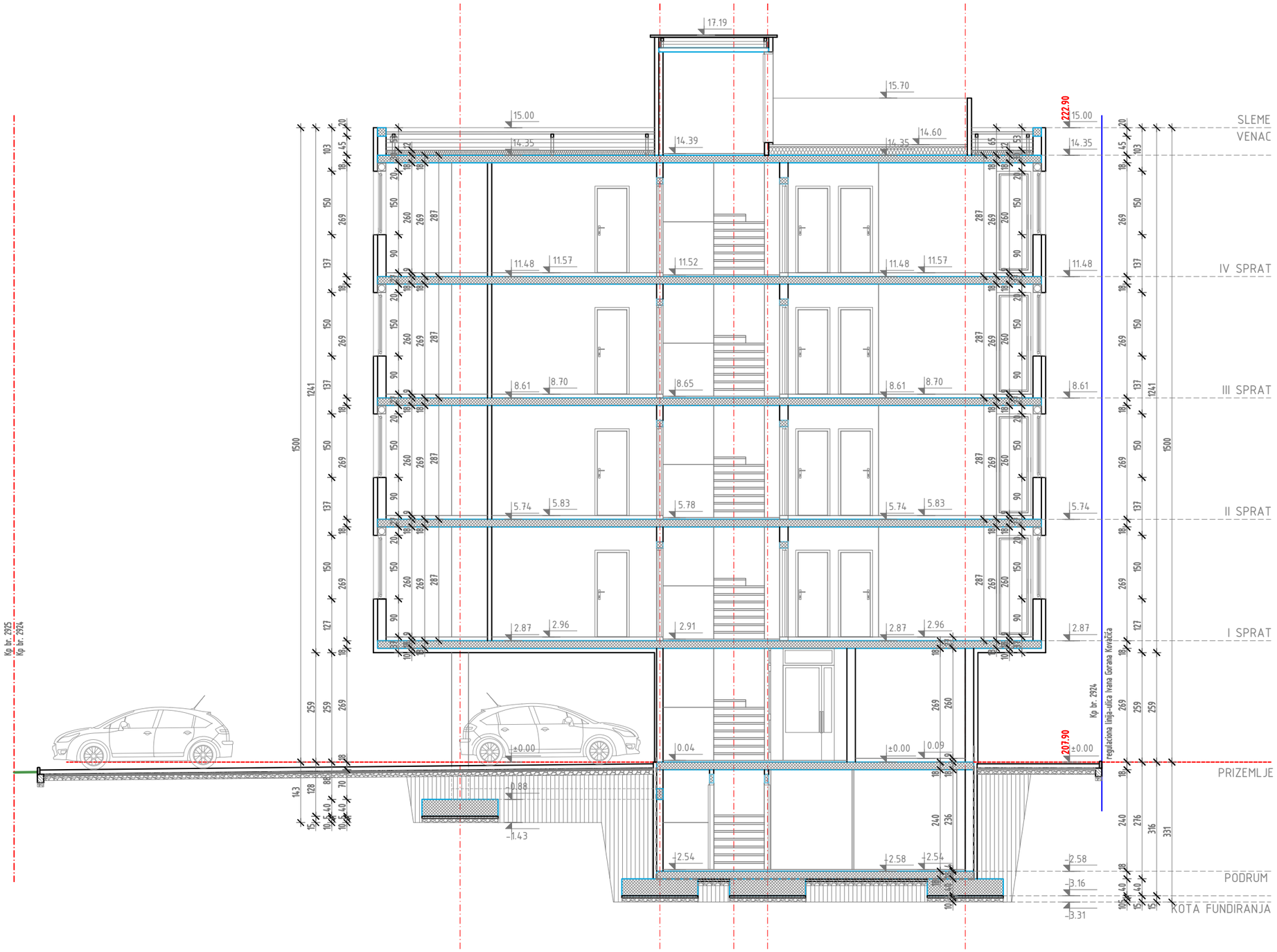

PRESEK A - A

Oznaka: IDR	Projekat: 0 - GLAVNA SVESKA		Registarski broj: 2/XII-2024-0	ARHITEKTONSKI PROJEKTNI BIRO
Glavni projektant: dipl.inž.arh. Danijela Gonev-Aranđelović broj licence 300 A00714 19		Investitor: "TEAM CONSTRUCTION 018" DOO Donje Brijanje Donje Brijanje bb, Leskovac		D CREATIVE
		Objekat: STAMBENI OBJEKAT, Po+P+4, u Nišu u ul. Ivana Gorana Kovačića br.13 , na k.p. br. 2924 KO Niš-Pantelej		Danijela Gonev-Aranđelović PR
Odgovorni projektant: dipl.inž.arh. Danijela Gonev-Aranđelović broj licence 300 A00714 19		Sadržaj: PRESEK A - A		NIŠ, Janisa Janulisa 22a
Saradnik:		Datum: 12.2024. god.	Razmera: 1:100 / List: 10	T: +381.60.536.4200

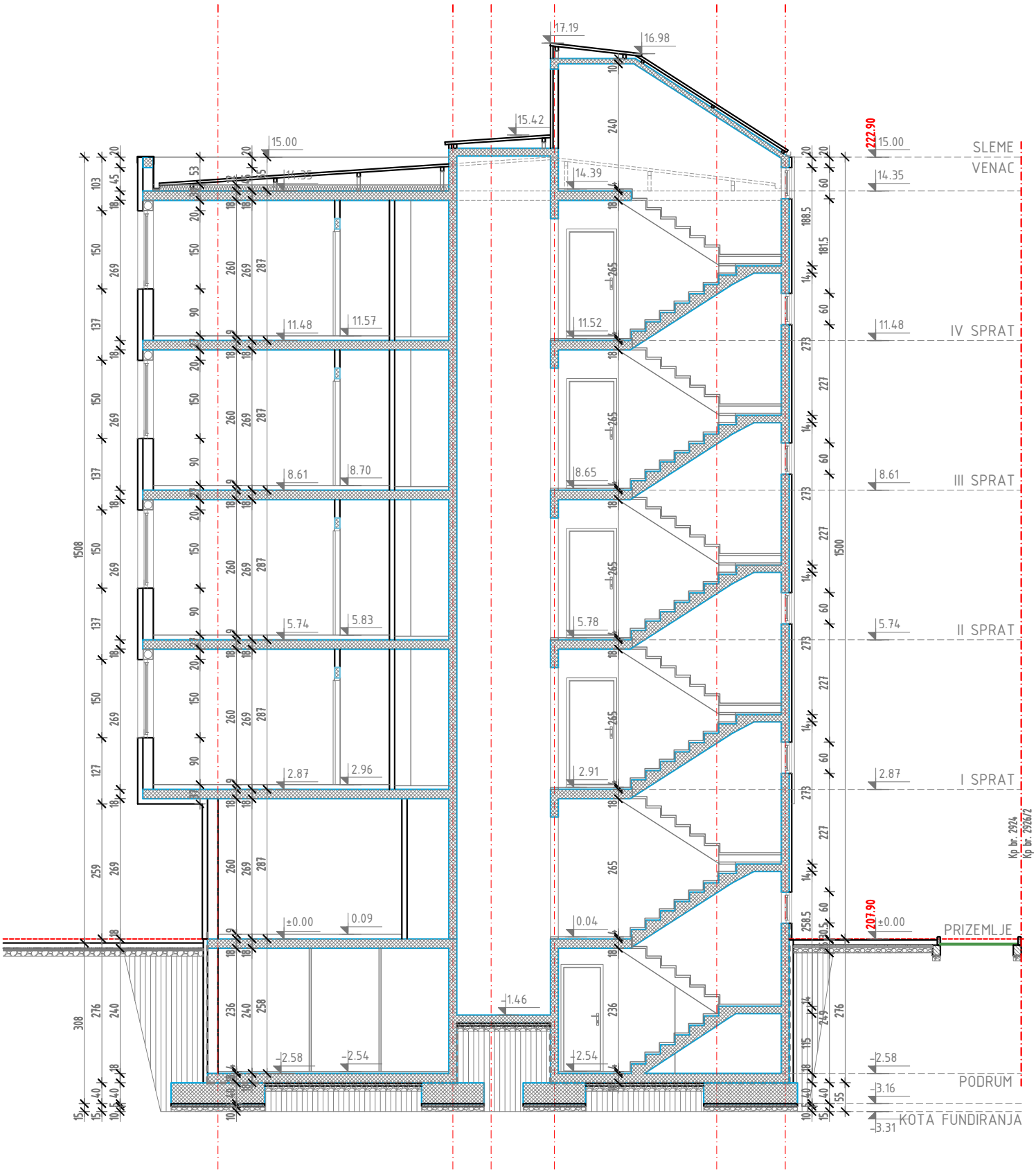

PRESEK B - B

Oznaka: IDR	Projekat: 0 - GLAVNA SVESKA	Registarski broj: 2/XII-2024-0	ARHITEKTONSKI PROJEKTNI BIRO
Glavni projektant: dipl.inž.arh. Danijela Gonev-Aranđelović broj licence 300 A00714 19	Investitor: "TEAM CONSTRUCTION 018" DOO Donje Brijanje, Donje Brijanje bb, Leskovac		D CREATIVE
Odgovorni projektant: dipl.inž.arh. Danijela Gonev-Aranđelović broj licence 300 A00714 19	Objekat: STAMBENI OBJEKAT, Po+P+4, u Nišu, u ul. Ivana Gorana Kovačića br.13 , na k.p. br. 2924 KO Niš-Pantelej		Danijela Gonev-Aranđelović PR
	Sadržaj: PRESEK B - B		NIŠ, Janisa Janulisa 22a
Saradnik:	Datum: 12.2024. god.	Razmera: 1:100 / List: 11	T: +381.60.536.4200